BOLETÍN INFORMATIVO AMBIENTAL- AEROPUERTO INTERNACIONAL EL DORADO

Centro de Monitoreo Aéreo Ambiental -

I -2023

Unidad Administrativa Especial de Aeronáutica Civil

Volumen 4

AERONÁUTICA CIVIL
UNIDAD ADMINISTRATIVA ESPECIAL

VUELO AC2C3C
SEGUIMOS TRANSFORMANDO VIDAS Y SUEÑOS

Sistema de Vigilancia y Control Ambiental

Applus+ K2

AERONÁUTICA CIVIL
UNIDAD ADMINISTRATIVA ESPECIAL

Contenido

1 Unidad Administrativa Especial Aeronáutica Civil (UAEAC)

2 Seguimiento y cumplimiento a la Licencia Ambiental

3 Centro de Monitoreo Aéreo Ambiental - AmbiensQ Aero: Tu Acceso a la Información del CMAA

4 Vigía Ambiental

5 Componente social territorio El Dorado

6 PQR's Primer Semestre 2023

7 Actualización Rutas Aéreas

AERONÁUTICA CIVIL
UNIDAD ADMINISTRATIVA ESPECIAL

VUELO AC2C3C
SEGUIMOS TRANSFORMANDO VIDAS Y SUEÑOS

Sistema de Vigilancia y Control Ambiental

Applus K2

UNIDAD ADMINISTRATIVA ESPECIAL AERONAUTICA CIVIL (UAEAC)

Aerocivil 100 años

Al fundarse en 1919 es la primera Empresa Comercial de Aviación en el País, el Estado vio la necesidad de crear un organismo cuyo objetivo estuviera enel control de la Aviación en todos los aspectos. Por medio de la ley 126 de 1919 se autorizó por primera vez al poder Ejecutivo para que reglamentara todo lo relacionado con la aeronavegación.

La Dirección General de la Aeronáutica Civil funcionó como dependencia del Ministerio de Guerra de la Dirección General de la Aviación Militar.

El rápido avance tecnológico hizo pensar en la necesidad de crear un organismo nacional encargado del control y prestación de servicios de aeródromos y aeronavegación para ejercer un control directo del espacio aéreo en razón de la seguridad que demanda la defensa de la soberanía nacional.

Para tal fin, la nación optó por comprar los aeródromos ya existentes, la mayoría de éstos de propiedad de Avianca, con todas las instalaciones de radioayudas de navegación y comunicación, además de la construcción y mantenimiento de nuevos aeropuertos y la adquisición de equipos de radioayudas y servicios aeroportuarios, para su normal funcionamiento.

SEGUIMIENTO Y CUMPLIMIENTO A LA LICENCIA AMBIENTAL

La Aeronáutica Civil se compromete con un estricto seguimiento y cumplimiento de su licencia ambiental. Esto implica la realización de actividades dedicadas a supervisar y mantener los componentes biótico, abiótico y sociales del área de influencia. El informe generado a partir de estas actividades son presentados ante la Autoridad Nacional de Licencias Ambientales (ANLA), con el objetivo de informar sobre el estado actual de la licencia y asegurar que se están tomando las medidas adecuadas para preservar el equilibrio ambiental y el bienestar de la comunidad.

Actividades

- La Unidad Administrativa Especial de Aeronáutica Civil prioriza la Gestión Ambiental y la prevención del Peligro Aviario en sus acciones.
- Da cumplimiento con las regulaciones nacionales e internacionales relacionadas con el transporte aéreo
- Temas de saneamiento, infraestructura y Cuidado ambiental
- Gestión social

Informe de Cumplimiento Ambiental

- Es presentado ante la ANLA semestralmente.
- Se describen actividades realizadas durante el periodo de reporte.
- Da seguimiento a los actos administrativos.
- Para el periodo de Enero a Junio de 2023, se presentó el ICA # 17, el cual esta en proceso de revisión por parte de la ANLA.

CENTRO DE MONITOREO AÉREO AMBIENTAL (CMAA)

El **Sistema de Vigilancia y Control Ambiental (SVCA)** fue optimizado y transformado en el **Centro de Monitoreo Aéreo Ambiental (CMAA)** del Aeropuerto Internacional El Dorado a partir de marzo de 2023. Se trata de un sistema a nivel mundial que integra parámetros ambientales y operacionales de manera integral. En el sitio web oficial de la Aerocivil, los usuarios podrán visualizar en tiempo real indicadores de acústica, contaminación atmosférica, condiciones meteorológicas, datos operacionales y atención de PQRS.

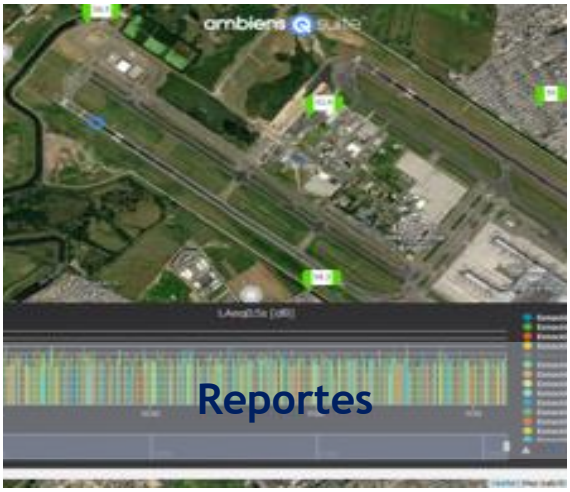

GESTIÓN DEL RUIDO

La Aerocivil, está comprometida con la sostenibilidad ambiental de la aviación. Una de las principales preocupaciones en este ámbito es la contaminación acústica generada por las aeronaves.

Para mitigar el ruido aeroportuario, la Aerocivil implementa una serie de acciones y programas, que se basan en los siguientes principios:

Innovación

- Busca constantemente nuevas tecnologías y métodos para reducir el ruido de las aeronaves.

Enfoque integral

- La mitigación del ruido debe ser un esfuerzo conjunto de todos los actores involucrados, incluyendo las aerolíneas, los aeropuertos y las comunidades vecinas.

Transparencia

- Brinda información clara y oportuna sobre las acciones que realiza para mitigar el ruido.

Algunas de las acciones y programas que implementa la Aerocivil son:

Establecimiento de normas y regulaciones

- Establece normas y regulaciones que limitan el nivel de ruido que pueden generar las aeronaves.

Incentivos a la innovación

- Ofrece incentivos a las aerolíneas y fabricantes de aeronaves para que desarrollen tecnologías más silenciosas.

Monitoreo del ruido

- Realiza un monitoreo continuo del ruido en los entornos aeroportuarios.

Educación y sensibilización

- Brinda educación y sensibilización a las comunidades vecinas sobre el ruido aeroportuario.

REPORTES

El CMAA, permite detectar, medir y asociar en tiempo real los Indicadores Ambientales producto de la operación aeroportuaria en lado aire y lado tierra del Aeropuerto Internacional El Dorado de la Ciudad de Bogotá D.C. Asimismo, se establece una continuidad al Sistema de Vigilancia y Control Ambiental, de conformidad a las obligaciones y requerimientos establecidos en la licencia ambiental.

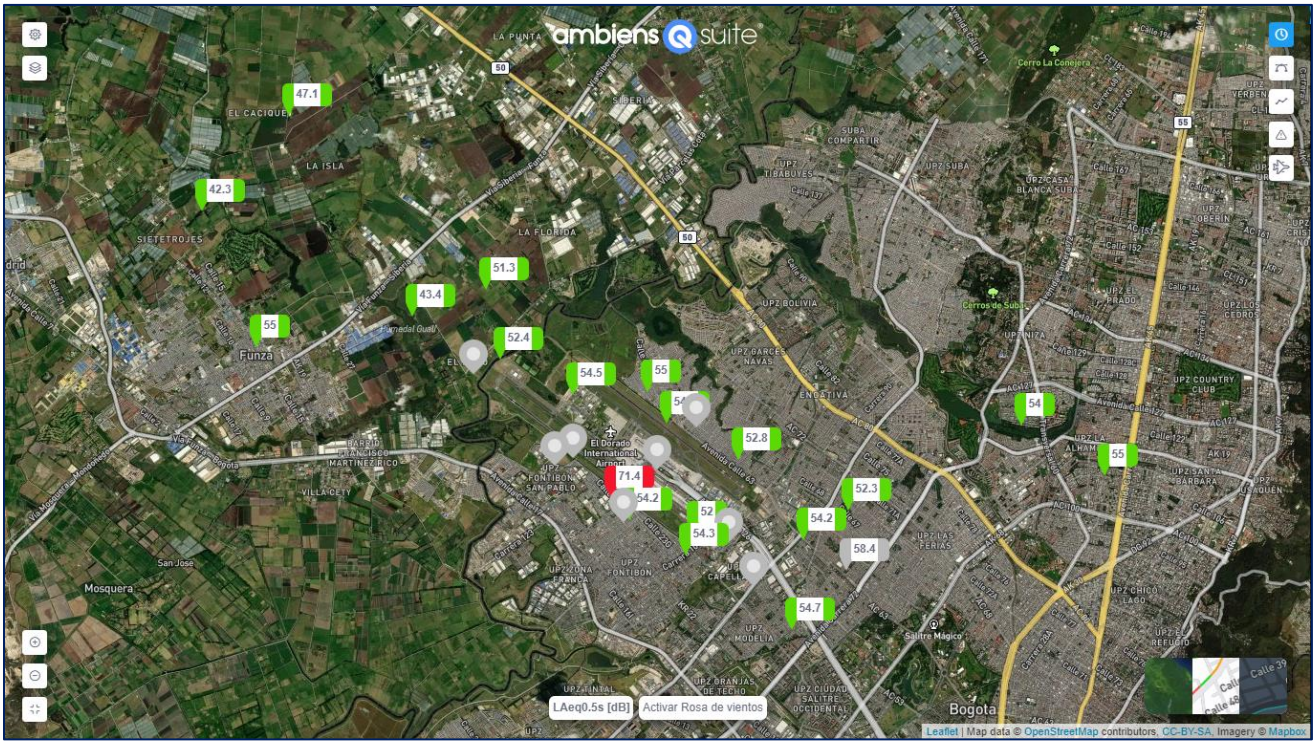

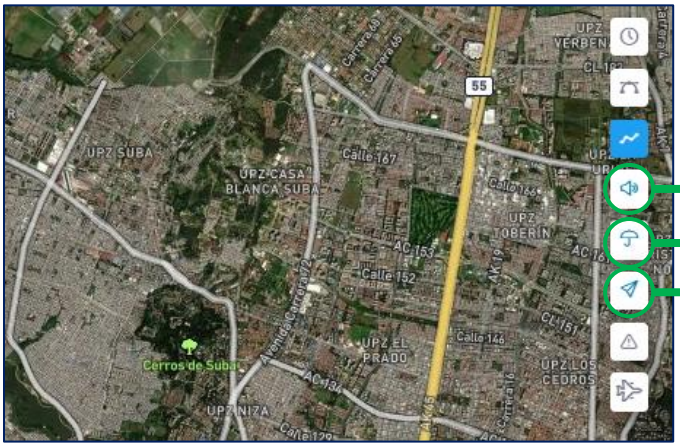

REGISTRO DE PQR

El Centro de Monitoreo Aéreo Ambiental (CMAA) ofrece una forma más sencilla y veloz de registrar tus Peticiones, Quejas o Reclamos (PQR). Aquí te explicamos cómo hacerlo en pocos pasos.

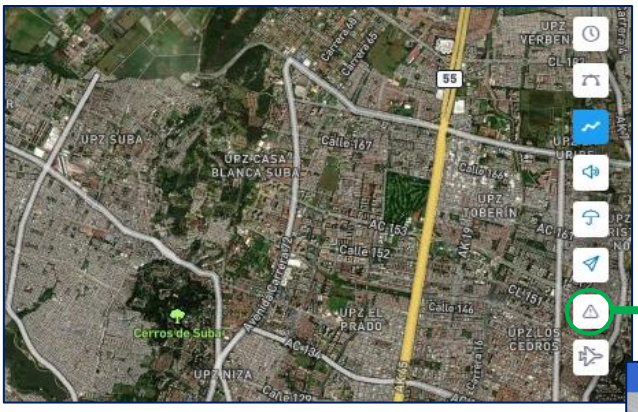

Registrar PQR

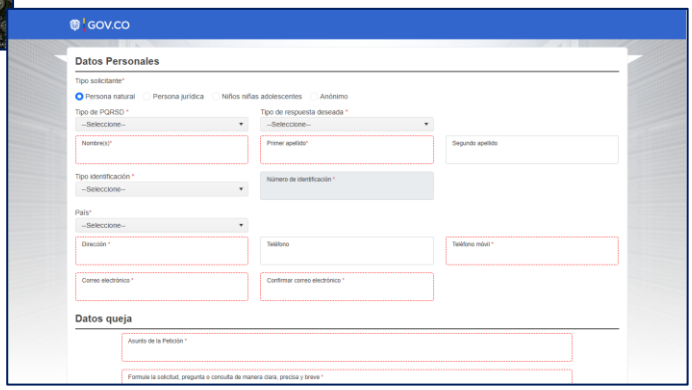

Accede a la Página de Aerocivil

Dirígete a la Sección de Gestión de Ruido
Accede al Centro de Monitoreo Aéreo Ambiental

Utiliza AmbiensQ
Al abrir el CMAA, te llevará a una ventana de AmbiensQ, la herramienta que facilita el registro.

Selecciona "Registrar PQR“
En la esquina superior derecha de la ventana, encontrarás una pestaña llamada "Registrar PQR". Haz clic en ella.

AMBIENSQ AERO: TU ACCESO A LA INFORMACIÓN DEL CENTRO DE MONITOREO AERO AMBIENTAL

AmbiensQ Aero es una aplicación que se encuentra en la fase final de pruebas. Está diseñada para funcionar en dispositivos Android e iOS. Tiene como objetivo brindar acceso a información relevante del Centro de Monitoreo Aéreo Ambiental (CMAA) de manera sencilla y práctica.

ambiensQ suite®
Environmental Management System

- **Seguimiento de Rutas de Aeronaves:**

Permite realizar un seguimiento básico de las rutas de vuelo de las aeronaves, brindándote información útil sobre su ubicación y trayectoria.

- **Consulta de Datos de Medición:**

Accede a datos precisos sobre mediciones de ruido, calidad del aire y condiciones meteorológicas. Esta función te proporciona información detallada y actualizada.

- **Acceso Rápido a PQR de Aerocivil:**

Con un solo clic, podrás acceder directamente al sitio web de Peticiones, Quejas y Reclamos (PQR) de Aerocivil para realizar tus consultas o reportes.

- **Información y Eventos de Aerocivil:**

Mantente al día con los eventos y noticias publicados por Aerocivil a través de AmbiensQ Aero. Esta función te mantiene informado.

- **Diligenciamiento de Encuestas Configuradas:**

Participa en encuestas específicamente diseñadas para obtener tu opinión y retroalimentación sobre diversos temas relacionados con el CMAA.

VIGÍA AMBIENTAL

Es una innovación urbana inteligente y versátil que usa sensores para recopilar datos sobre el entorno entregando información del clima, la calidad del aire y el ruido en el entorno. Estos datos se almacenan y son procesados por un software avanzado en la nube. La información resultante se comparte en tiempo real con la industria, la comunidad y autoridades locales, lo que facilita tomar decisiones más rápidas y precisas.

El Vigía Ambiental estará operativo a partir del segundo semestre de 2023 y tendrá ubicaciones en

Engativá

Funza

Fontibón

Nota: *Las imágenes proporcionadas en esta página son meramente ilustrativas y se presentan a título de referencia.*

COMPONENTE SOCIAL TERRITORIO EL DORADO

ACCIONES DEL EQUIPO SOCIAL EN EL ÁREA DE INFLUENCIA

Información Clara y Accesible para Comunidades y Autoridades	Fomentar la participación entre entidades para facilitar el acceso a diversas fuentes de información. Esto permite desarrollar nuevas habilidades en asuntos socioambientales vinculados a la operación en el territorio.
Respuestas Abiertas y Transparentes	Atención de inquietudes, quejas y reclamaciones, proporcionando información detallada, tomando medidas para fortalecer las acciones ya emprendidas y realizando visitas de campo para mejora la toma de decisiones.
Acciones Conjuntas y Sostenibles	Promover procesos de formación, mejoras y seguimientos con la comunidad en relación a los monitoreos ambientales. También brindamos apoyo a iniciativas dirigidas a abordar los impactos derivados de la operación aérea.
Intercambio de conocimientos	Trabajamos de la mano con los actores del territorio, aprovechando sus avances para llevar a cabo acciones conjuntas.

COMPONENTE SOCIAL

La **Resolución 1728 de octubre de 2021** marca un hito en la modificación de la licencia ambiental partir de adoptar nueves medidas que permitan alcanzar una operación armónica y sostenible. Para ello, Presentamos las fichas de Plan de Manejo Ambiental (PMA) para el componente socioeconómico, el cual esta bajo el seguimiento directo de la Autoridad Nacional de Licencias Ambientales.

Fichas Componente Socioeconómico del PMA Resolución 1728 de 2021

PGS-1
Sensibilización y educación

PGS-2
Información y comunicación

PGS-3
Apoyo en cogestión interinstitucional y comunal

GESTIÓN SOCIAL

A partir de la actualización del Estudio de Impacto Ambiental (EIA) del año 2020 realizado por la Aeronáutica Civil, se definió el área de influencia socioeconómica de acuerdo con el indicador acústico LDN de 65dB, y que por traslape de la curva de ruido incluiría algunas unidades territoriales menores siguiendo los términos de referencias para construcción y operación de aeropuertos Internacionales de ANLA.

El equipo de gestión social desarrolla sus actividades en 89 unidades territoriales menores discriminadas desde las localidades de Fontibón, Engativá y el municipio de Funza en su área rural.

Fontibón

UPZ

- 75
- 76
- 114
- 115
- 117

BARRIOS

- Dentro de las 5 UPZ el AI se compone de 40 barrios

Engativá

UPZ

- 30
- 31
- 73
- 74
- 116
- 26

BARRIOS

- Dentro de las 6 UPZ el AI se compone de 45 barrios

Funza

4 VEREDAS

NOTA: Dentro del AI del Aeropuerto, se integran únicamente algunos barrios de las UPZ mencionadas, no la totalidad de las UPZ, para ver el Detalle de los barrios del AI **Consulte la resolución 1728 de 2021**

AERONÁUTICA CIVIL
UNIDAD ADMINISTRATIVA ESPECIAL

SOCIALIZACIÓN DEL CENTRO DE MONITOREO AERO AMBIENTAL

¡Avances Locales en el Primer Semestre del 2023!

En el primer semestre de 2023, con la puesta en marcha del **Centro de Monitoreo Aéreo Ambiental**, se da inicio con la proyección del cronograma para la socializar el nuevo CMAA durante el periodo del 2023.

Las socializaciones se llevarán a cabo con los lideres de la localidad, de manera **presencial y virtual**, favoreciendo la participación e información de los lideres comunitarios de todas las unidades territoriales.

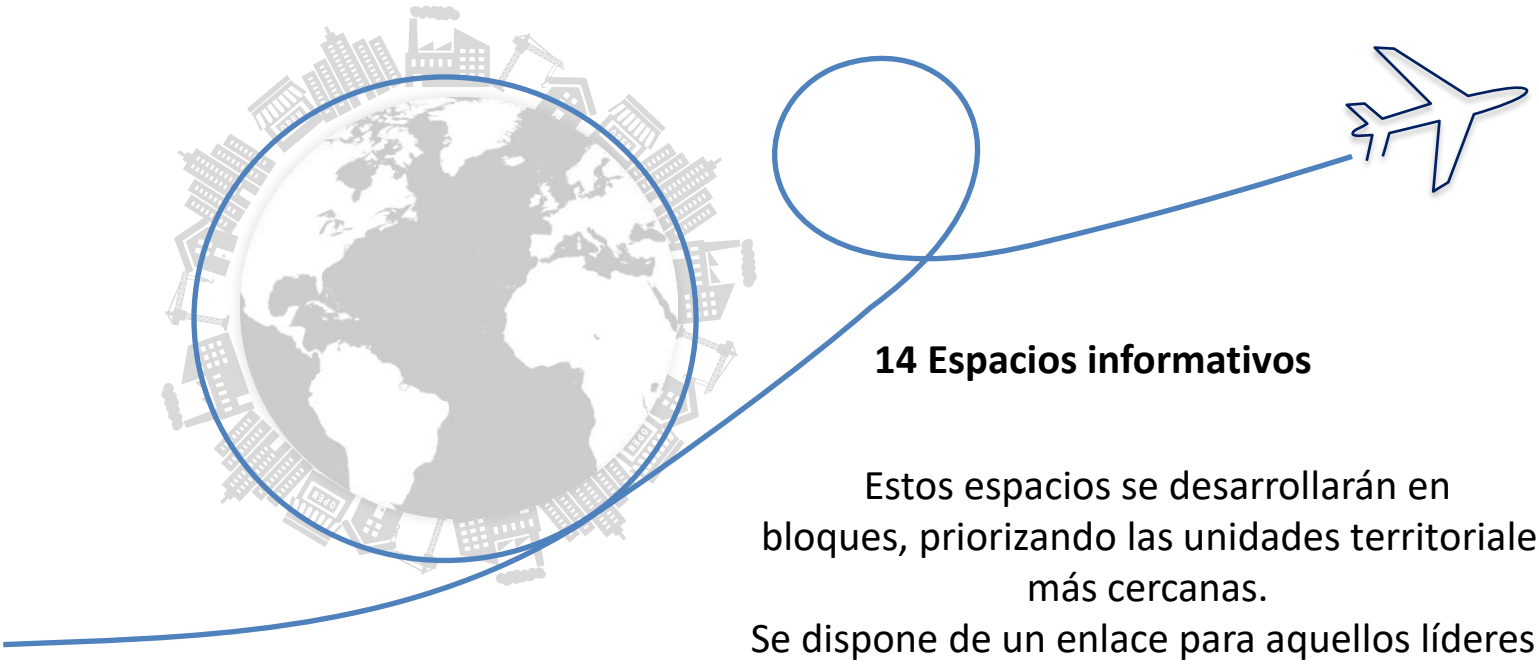

14 Espacios informativos

Estos espacios se desarrollarán en bloques, priorizando las unidades territoriales más cercanas.
Se dispone de un enlace para aquellos líderes y autoridades que quieran participar.

AERONÁUTICA CIVIL
UNIDAD ADMINISTRATIVA ESPECIAL

VUELO AC2C3C
SEGUIMOS TRANSFORMANDO VIDAS Y SUEÑOS

Sistema de Vigilancia y Control Ambiental

Applus+ K2

ACCIONES DEL GRUPO DE GESTIÓN SOCIAL

Fontibón

Durante mayo, junio y julio en Fontibón, se realizaron visitas a líderes de Juntas de Acción Comunal. Se brindó apoyo al Consorcio Kappa, se llevó a cabo una socialización del CMAA y se sostuvieron reuniones con autoridades locales y organizaciones comunitarias. También se ofreció un taller sobre el fortalecimiento de emprendimientos locales en redes sociales.

Funza

En abril, se coordinó y ejecutó una reunión con las Autoridades Locales para establecer estrategias de articulación interinstitucional. Así mismo, a lo lardo del semestre se realizaron visitas de seguimiento a las Estaciones de Monitoreo de Ruido Inteligente (EMRI) ubicadas en el municipio, junto con recorridos por los buzones PQRS ubicados en el Área de Influencia. Del mismo modo, en el mes de Junio se realizó una socialización del Centro de Monitoreo Aéreo Ambiental (CMAA) con el Municipio de Funza.

Engativá

En la localidad de Engativá en el transcursos del primer semestre del 2023 se continuó el acercamiento con las autoridades locales y lideres comunitarios. Así mismo, se realizó la primera vista al interior del Aeropuerto Internacional El Dorado, contando con la participación de los integrantes del barrio Villa El Dorado. Por otra parte, se contó con la participación en el programa Aula Ambiental de la Alcaldía Local de Engativá en tres colegios del AI. Finalmente, se realizó un trabajo interinstitucional con la Alcaldía Local para él bici recorrido por el humedal Jaboque.

¡Estos logros reflejan un avance notable en nuestra labor durante el primer semestre de 2023!

PRESENTACIÓN DEL CMAA EN EL MUNICIPIO DE FUNZA

De esta manera, en el primer semestre se aborda el primer espacio de información y comunicación con los Líderes del Área de Influencia, integrantes del Comité Municipal ***para el Estudio De Los Impactos Generados por el Funcionamiento del Aeropuerto Internacional El Dorado En El Municipio De Funza Cundinamarca*** y la Autoridad Municipal de Funza.

La finalidad de estos espacios informativos es presentar el Centro de Monitoreo Aero Ambiental (CMAA) del Aeropuerto Internacional El Dorado. Así mismo, la transición del Sistema de Vigilancia y Control Ambiental, las etapas del desarrollo, explicación de las **Plataformas AmbiensQ y Aerovision**, la ubicación de los equipos y la implementación de los Vigías Ambientales.

COMITÉ COMUNITARIO AEROPORTUARIO (CCA)

El CCA, compuesto por las comunidades del Área de Influencia del Aeropuerto Internacional El Dorado, se establece como un pilar fundamental, actuando como garantes, vigilantes y multiplicadores en la gestión. Por otra partes, realiza un seguimiento continuo a los impactos derivados de la operación aérea. Su misión es asegurar la participación activa y representativa de las comunidades en los espacios generados por la Aerocivil.

En el mes de abril, se dio continuidad al proceso de consolidación del CCA, convocando a las comunidades del área de influencia de la terminal aérea. Durante dicha jornada se contó con la participación 69 personas pertenecientes a las localidades de Engativá, Fontibón y un representante de Teusaquillo.

Bajo la dirección de los funcionarios Johan Núñez y Manuel Tapasco, se presentó la Resolución 1728 de 2021 y se discutió la transición del **Sistema de Vigilancia y Control Ambiental** al innovador **Centro de Monitoreo Aéreo Ambiental**.

Los Compromisos establecidos con las comunidades; el primero es Participar en las Mesas de Trabajo con Secretarias Distritales y Establecer temas específicos para el próximo encuentro.

CONTROL DE PLAGAS EN EL DORADO

El Grupo de **Gestión Ambiental y Control de Fauna** de la Aeronáutica Civil tiene un compromiso claro: comunicar de forma efectiva las acciones que beneficien la continua información a las comunidades.

Desde mayo, se detectaron focos de vectores cerca de las pistas norte y sur del Aeropuerto Internacional El Dorado. Para garantizar la operación aérea y mitigar riesgos de salud a la comunidad vecina. Razón por la cual, se ha puesto en marcha el Programa de ***Manejo Integrado de Plagas.***

El 16 y 20 de junio, las profesionales sociales del Centro de Monitoreo Aéreo Ambiental, realizaron la gestión para el acercamiento a los puntos establecidos por el Consorcio Kappa para la implementación del programa.

Esta iniciativa no solo impacta al aeropuerto, sino también en los barrios cercanos. La información se compartió en Villa Gladys (Engativá) y en los barrios Las Brisas, Selva Dorada, Los Cámbulos y El Refugio (Fontibón). Se realizaron charlas informativas y se distribuyeron volantes para asegurar que la información llegue a todas las comunidades.

TALLER DE RECUPERACIÓN DE VIDRIO Y TERRARIOS

Durante el primer semestre del 2023, se da inicio al primer ciclo ambiental con la propuesta de intervención y capacitación en las comunidades del área de influencias, donde se observa la existencia de una cohesión social, interés y **participación** por parte de su comunidad.

Estos talleres tuvieron dos objetivos esenciales: **fomentar la economía circular** en las comunidades a partir de la reutilización del vidrio, aprovechando los envases que a menudo terminan en los rellenos sanitarios; y **generar espacios de cohesión social**, que lleguen a impactar en el largo plazo a las comunidades del AI.

Más de 50 botellas de vidrio recuperadas

Creación de Terrarios

Esta primera parte del ciclo se centra puntualmente en la elaboración de terrarios a través de envases recuperados de vidrio, el cual es, un material totalmente inorgánico. Sin embargo, 1 botella de vidrio tarda 4000 años en degradarse. El vidrio es un material muy frágil, y al mismo tiempo resistente. Por tal motivo, la naturaleza necesita 40 siglos para transformarlo y es importante que se deposite en los lugares adecuados para su gestión. “El vidrio es 100% reciclable.

Este evento dio vida a iniciativas ecológicas y creativas de gran relevancia para las comunidades como para si entorno.

ESPACIOS DE INFORMACIÓN CON AUTORIDADES LOCALES, ORGANIZACIONES Y COMUNIDADES

A partir de los espacios de información con autoridades locales, organizaciones y comunidades, en el primer semestre se cumplió al llamado de las Juntas Administradoras Locales de las localidades de Engativá y Fontibón, para dar respuesta a las restricciones aeronáuticas para el uso de suelos en áreas aledañas al Aeropuerto Internacional El Dorado. Así mismo, se aclaró el rol que tiene La Aerocivil en el proyecto denominado Distrito Aeroportuario del cual no hace parte esta entidad, en este espacio se participó junto a la Secretaria Distrital de Planeación, donde cada entidad rindió cuentas según sus competencias.

JAL Fontibón
18 abril 2023

Alcaldía Engativá
14 junio 2023

JAL Engativá
12 de mayo23

Alcaldía Fontibón
3 mayo 2023

Así mismo, se abordó la Transición **del Sistema de Vigilancia y Control Ambiental** al **Centro de Monitoreo Aéreo Ambiental**. Se socializo la normativa actual de la **Resolución 1728 de 2021**, que modifica la Licencia Ambiental del Aeropuerto Internacional El Dorado bajo la resolución 1034.

AERONÁUTICA CIVIL
UNIDAD ADMINISTRATIVA ESPECIAL

TRANSFORMANDO HUERTAS, TRANSFORMANDO VIDAS

Desde la Aeronáutica Civil y continuando con el dialogo con las comunidades, se establece la vinculación del programa de Mantenimiento del Río Bogotá, para el fortalecimiento y el mejoramiento de 4 huertas urbanas en el área de influencias del Aeropuerto Internacional El Dorado. El desarrollo de estas acciones permiten beneficiaran a las comunidades vecinas de la terminal aérea.

Es así que, se realiza un análisis de posibles huertas a intervenir, a partir de este análisis se establece el desarrollo del proyecto en los barrios Viña del Mar y Los Álamos en la Localidad de Engativá, y en los barrios Cofradía y la Zelfita de la Localidad de Fontibón, estas no solo sirven como espacios para fomentar la interacción social, sino que también contribuyen a la preservación de técnicas agrícolas populares mediante el enriquecedor encuentro entre diferentes generaciones y culturas.

Huerta Los Álamos

¡Una experiencia que fortalece el tejido comunitario!

Huerta La Zelfita

Huerta Cofradía

AERONÁUTICA CIVIL
UNIDAD ADMINISTRATIVA ESPECIAL

VUELO AC2C3C
SEGUIMOS TRANSFORMANDO VIDAS Y SUEÑOS

Sistema de Vigilancia y Control Ambiental

Applus+ K2

AERONÁUTICA CIVIL
UNIDAD ADMINISTRATIVA ESPECIAL

VISITANDO EL AEROPUERTO INTERNACIONAL EL DORADO

El día 7 de junio del 2023, en colaboración con OPAIN, se realizó la primera visita del año a las instalaciones del Aeropuerto Internacional El Dorado, con la participación de los residentes del barrio Villas El Dorado Norte de la localidad de Engativá.

Durante este recorrido, se visitó **la Planta de Tratamiento de Aguas Residuales (PTAR)** y la **Estación de Clasificación y Aprovechamiento de Residuos (ECAR).** El Operador *Interaseo SAS ESP* brindó información sobre el proceso y funcionamiento de ambas instalaciones, que gestionan tanto el agua como los desechos generados por el aeropuerto, incluyendo locales comerciales, áreas públicas y aeronaves.

Además, para enriquecer la experiencia, se socializó información sobre el Recinto Prueba de Motores, una infraestructura innovadora encargada de mitigar el ruido durante la prueba a bajo, medio y alta potencia de los motores y mantenimiento en tierra.

Residentes del barrio Villas El Dorado Norte

Localidad Engativá

REUNIÓN CON LAS AUTORIDADES DE FUNZA

Con el fin de fortalecer la cogestión interinstitucional, se propició un espacio de concertación con la Autoridad Ambiental del municipio de Funza.

El objetivo, fue generar espacios articulados para la difusión de información sobre los avances y compromisos pactados en el marco de la Resolución 1728 de 2021. Este encuentro, tuvo lugar el 10 de abril de 2023 en las oficinas de la Secretaría de Ambiente y Protección Animal.



Recorrido por las Estaciones de Monitoreo de Ruido Inteligente (EMRI) en Funza

En aras de vincular a los representantes de las instituciones y comunidad a las acciones de seguimiento y mitigación; se realizan recorridos de verificación del correcto funcionamiento de la Estaciones (EMRI) ubicadas en el Municipio de Funza en compañía de funcionarios delegados por la secretaría de Ambiente y Bienestar Animal.

EMPRENDIENDO JUNTOS: CAPACITACIÓN EN REDES SOCIALES

En un esfuerzo colaborativo entre el Grupo de **Gestión Ambiental y Control Fauna** y el equipo social del **Centro de Monitoreo Aéreo Ambiental,** se han proporcionado herramientas para impulsar a las comunidades hacia un mejoramiento socioeconómico.

Una de las iniciativas surgidas de este acercamiento con líderes comunitarios fue una serie de capacitaciones en el uso efectivo de las redes sociales. El objetivo era potenciar los emprendimientos en el Área de Influencia del Aeropuerto Internacional El Dorado, en la Localidad de Fontibón.

Desde mayo, se ha brindado apoyo a los barrios *Ofir* y *El Trébol*, enfocándonos en el fortalecimiento de habilidades emprendedoras a través de la formación en el uso de redes sociales.

Para las mujeres a cargo de la **Huerta Comunitaria**, ha significado un paso adelante en su proyecto de soberanía alimentaria, la cual ha permitido aprovechar los productos cultivados.

En las primeras sesiones, nos centramos en resaltar la relevancia actual de plataformas como ***Instagram, Facebook*** **y** ***TikTok*** para promocionar emprendimientos.

Diseño de pagina en Instagram de la Hurta del Ofir El Trébol.

NUEVAS RUTAS EN AEROCIVIL

A partir del **constante trabajo de campo y reconocimiento del Área de Influencia,** se logra un acercamiento entre la Aeronáutica Civil y las Fundaciones: Furdir y Cacique, que a su vez invitan a la colaboración de la Fundación Hard Fight Colombia. (revisar y asegurase bien de los nombres de las fundaciones).

Fundación *Furdir*



Fundación *Hard Fight*

Estas instituciones se dedican a apoyar a la comunidad con diversidad funcional y comparten la misión de promover proceso de inclusión en diferentes espacios y escenarios para estas personas. **De esta manera se propicia la articulación y cogestión interinstitucional desde la Entidad**, generando espacios de aprendizajes, emprendimiento y dialogo constantes.

IMPACTO EDUCATIVO: AULA AMBIENTAL

Durante este período, el equipo del Centro de Monitoreo se sumergió en la estrategia del Aula Ambiental de la Alcaldía Local de Engativá. Este programa consistió en compartir experiencias enriquecedoras con estudiantes de colegios públicos y privados de la zona.

Colegio Cristiano Psicopedagógico Sinaí

Es una oportunidad valiosa para interactuar poblaciones de diversas edades y mostrarles las acciones que adelanta el Aeropuerto Internacional El Dorado.

Aula Ambiental junio 2023

Durante el primer periodo del 2023, el equipo se unió a esta iniciativa en los colegios Juan Bosco y el Colegio Cristiano Psicopedagógico Sinaí en el barrio Floridablanca.

Colegio Don Bosco

En cada encuentro, se interactuó con un estimado de entre 200 y 500 niños y niñas, generando un acercamiento significativo para la Entidad.

¡PEDALEO CULTURAL! SOCIALIZACIÓN EN BICI POR EL HUMEDAL JABOQUE, ENGATIVÁ

En el mes de junio, el grupo social de la **Unidad Especial Aeronáutica Civil** se unió a la Semana Cultural organizada por la Alcaldía Local de Engativá. En conmemoración del **Día Internacional de la Bicicleta**, participo con un punto de hidratación en un bici recorrido que se extendió desde el Parque Central de Engativá Pueblo hasta el Puente de Guadua en la Calle 80, alrededor del Humedal Jaboque.

Bici recorrido

Tanto jóvenes como adultos se unieron a este evento direccionado por la Alcaldía Local de Engativá. Durante la actividad se realiza la presentación del **Centro de Monitoreo Aéreo Ambiental** del Aeropuerto Internacional El Dorado.

El evento contó con la participación de entidades como la Policía Nacional, el Instituto Distrital de Cultura y Turismo y el Comité de Libertad Religiosa y Conciencia de la localidad de Engativá.

Humedal Jaboque

PQRS
PRIMER SEMESTRE 2023

El **primer semestre del 2023** estuvo marcado por un cambio en las rutas operativas de las aerolíneas a partir de diciembre de 2022. Esto resultó en un aumento en la recepción de PQRS, no solo en el Área de Influencia del Aeropuerto Internacional El Dorado, sino también en sectores previamente no afectados por las rutas.

Para abordar las inquietudes generadas por este cambio, se implementó una campaña de medición de ruido aeronáutico, con la instalación en febrero de la Estación de Medición de Ruido Inteligente mobil (ENRI 1) en el barrio Pasadena. Además, se propiciaron tres espacios de socialización para presentar los resultados de esta medición, los cuales tuvieron lugar los días 15, 20 y 21 de abril de 2023.

A continuación, presentamos el gráfico que resume el total de PQRS recibidas durante el primer semestre de 2023.

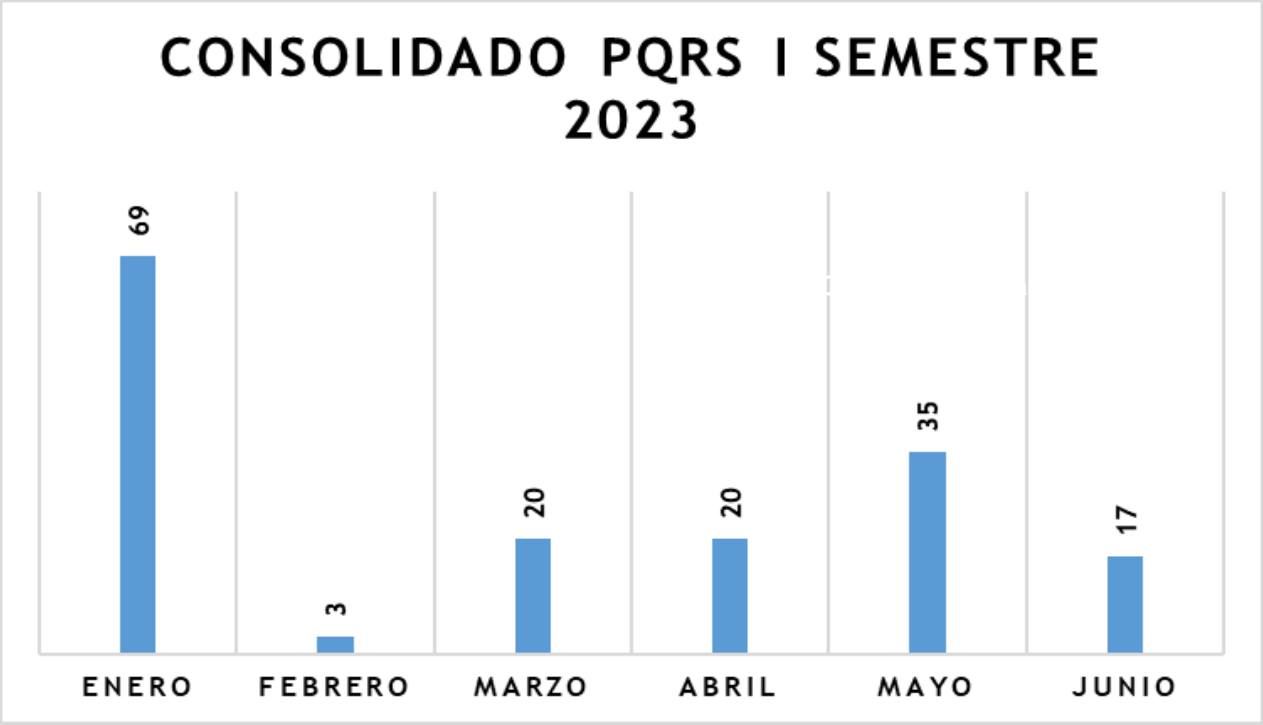

ANÁLISIS DE LAS PQRS DEL PRIMER SEMESTRE 2023

De la misma manera, el gráfico previo indica un segundo pico en mayo de 2023, con un total de 35 PQRS. Los meses de marzo, abril y junio mantuvieron un comportamiento estable en cuanto a la recepción de solicitudes, esto se dio tras el acercamiento con la población y el seguimiento a cada una de las PQR.

Es necesario destacar la atención oportuna brindada a cada una de las solicitudes. Se llevó a cabo |un minucioso análisis que consideró tanto el número de requerimientos recibidos como la curva de ruido y los cambios de trayectorias.

En la imagen se identifica la georreferenciación de todas las PQR interpuestas durante el primer semestre del 2023, según la base del sistema de datos gestionada por la Entidad.|

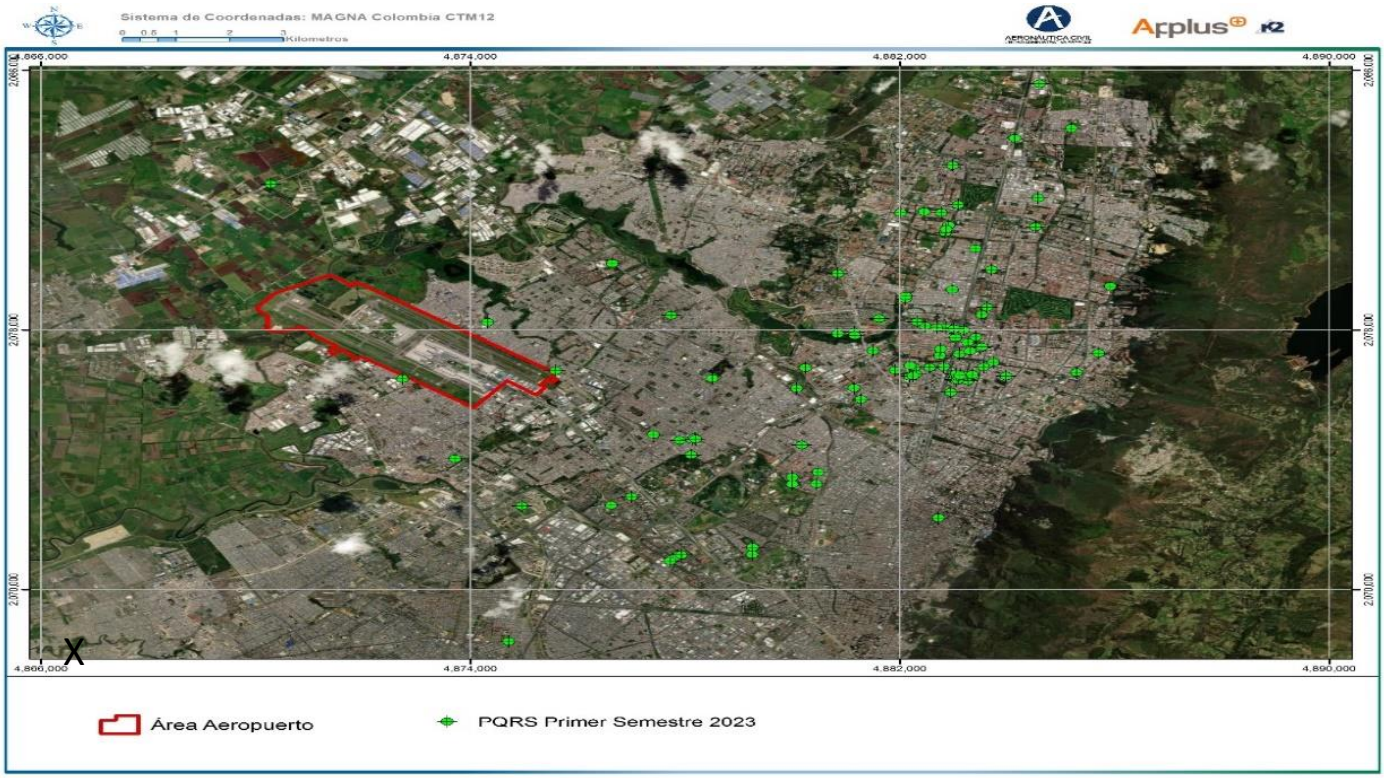

ACTUALIZACIÓN RUTAS AÉREAS

La Unidad Administrativa Especial Aeronáutica Civil, el 18 de mayo de 2023, a través del grupo de los Servicios de Información Aeronáutica de la Dirección de los Servicios a la Navegación Aérea, actualizó las cartas de navegación aérea de las rutas aéreas sobre la ciudad de Bogotá D.C, los cuales se encuentran en la Publicación de Información Aeronáutica (AIP). En esta publicación se encuentra la información aeronáutica permanente, así como los cambios temporales de larga duración. El AIP se divide en tres partes: Generalidades (GEN), En Ruta (ENR) y Aeródromos (AD). Las cartas de navegación en donde se indican las rutas aéreas que van desde y hacia el Aeropuerto Internacional El Dorado se encuentras publicada en la parte de aeródromos controlados, específicamente en el **AIP AD 2 SKBO.**

La actualización fue hecha siguiendo los lineamientos de seguridad operacional dados por la Organización de Aviación Civil Internacional (OACI), con el fin de cerrar riegos operacional existentes en las rutas aéreas que sobrevuelan todo Colombia y que conectan a los aeropuertos. La publicación de esta actualización fue realizada en el ciclos de publicaciones de información aeronáutica AIRAC AMDT 65/23.

A continuación se pueden observar las rutas áreas sobre la ciudad de Bogotá y el municipio de Funza. Las aeronaves que deban realizar sus procedimientos despegue, deberán seguir la rutas aéreas de color azul, violeta y naranja establecidas en las cartas de Navegación por de salida por instrumentos normalizada – SID/RNAV. Las aeronaves que realicen sus procedimientos de aproximación o aterrizaje deberán seguir las rutas aéreas de color verde y amarillo establecidas en la cartas de navegación de aproximación por instrumentos OACI - IAC y las cartas de navegación por procedimientos de vuelo visual RNP.

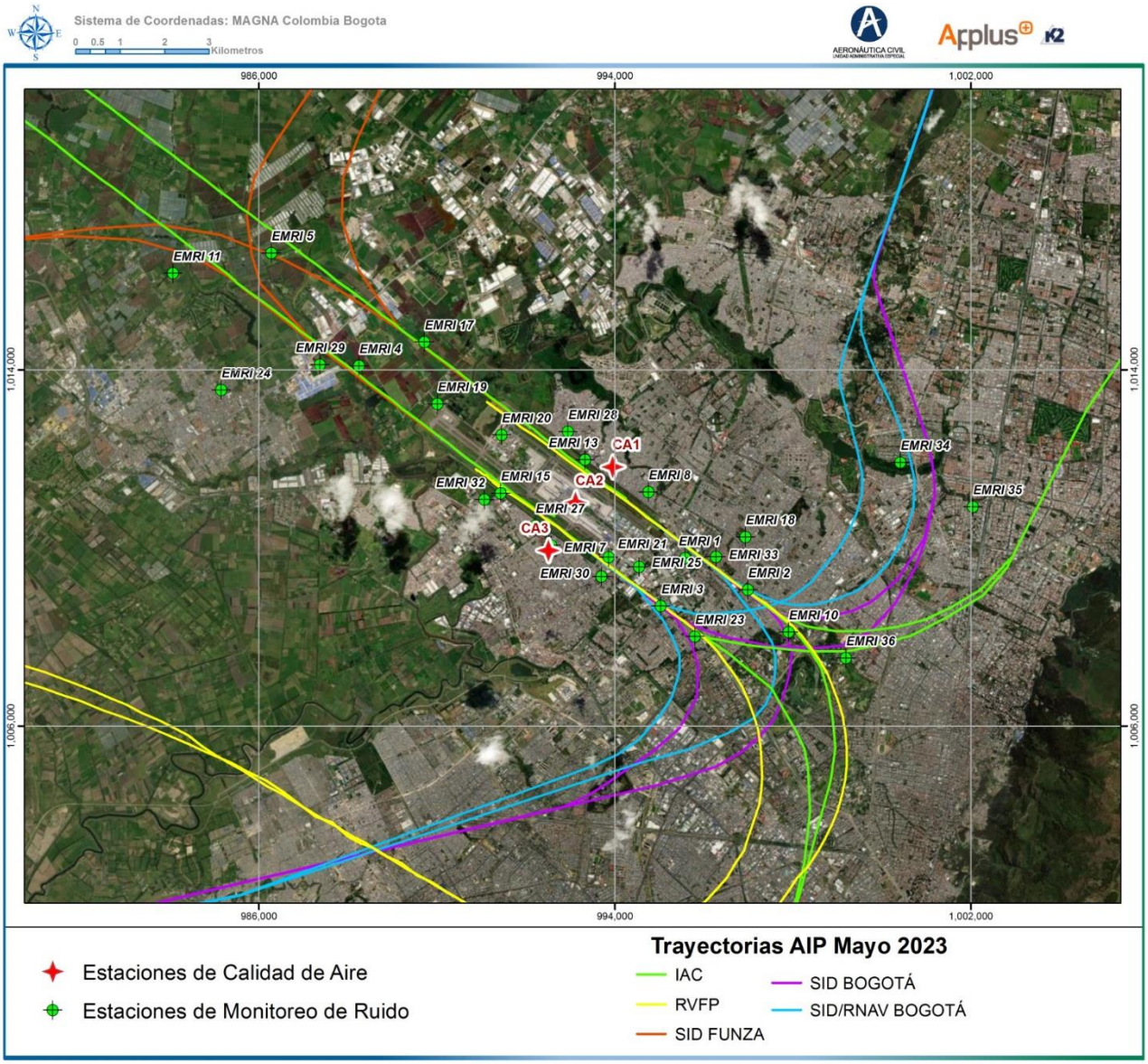

SI TIENEN DUDAS

PUEDEN COMUNICARSE

Sandra Rodríguez

320 9163105

sandra.rodriguez.r@k2ingenieria.com.co

Fontibón

Milena Murillo

310 2803999

milena.murillo@k2ingenieria.com.co

Engativá

Diana Hernández

320 9163132

diana.hernandez@k2ingenieria.com

Funza

AERONÁUTICA CIVIL
UNIDAD ADMINISTRATIVA ESPECIAL

2024

ENERO

L	M	X	J	V	S	D
1	2	3	4	5	6	7
8	9	10	11	12	13	14
15	16	17	18	19	20	21
22	23	24	25	26	27	28
29	30	31				

FEBRERO

L	M	X	J	V	S	D
			1	2	3	4
5	6	7	8	9	10	11
12	13	14	15	16	17	18
19	20	21	22	23	24	25
26	27	28	29			

MARZO

L	M	X	J	V	S	D
				1	2	3
4	5	6	7	8	9	10
11	12	13	14	15	16	17
18	19	20	21	22	23	24
25	26	27	28	29	30	31

ABRIL

L	M	X	J	V	S	D
1	2	3	4	5	6	7
8	9	10	11	12	13	14
15	16	17	18	19	20	21
22	23	24	25	26	27	28
29	30					

MAYO

L	M	X	J	V	S	D
		1	2	3	4	5
6	7	8	9	10	11	12
13	14	15	16	17	18	19
20	21	22	23	24	25	26
27	28	29	30	31		

JUNIO

L	M	X	J	V	S	D
					1	2
3	4	5	6	7	8	9
10	11	12	13	14	15	16
17	18	19	20	21	22	23
24	25	26	27	28	29	30

JULIO

L	M	X	J	V	S	D
1	2	3	4	5	6	7
8	9	10	11	12	13	14
15	16	17	18	19	20	21
22	23	24	25	26	27	28
29	30	31				

AGOSTO

L	M	X	J	V	S	D
			1	2	3	4
5	6	7	8	9	10	11
12	13	14	15	16	17	18
19	20	21	22	23	24	25
26	27	28	29	30	31	

SEPTIEMBRE

L	M	X	J	V	S	D
						1
2	3	4	5	6	7	8
9	10	11	12	13	14	15
16	17	18	19	20	21	22
23	24	25	26	27	28	29
30						

OCTUBRE

L	M	X	J	V	S	D
	1	2	3	4	5	6
7	8	9	10	11	12	13
14	15	16	17	18	19	20
21	22	23	24	25	26	27
28	29	30	31			

NOVIEMBRE

L	M	X	J	V	S	D
				1	2	3
4	5	6	7	8	9	10
11	12	13	14	15	16	17
18	19	20	21	22	23	24
25	26	27	28	29	30	

DICIEMBRE

L	M	X	J	V	S	D
						1
2	3	4	5	6	7	8
9	10	11	12	13	14	15
16	17	18	19	20	21	22
23	24	25	26	27	28	29
30	31					

AERONÁUTICA CIVIL
UNIDAD ADMINISTRATIVA ESPECIAL

Boletín Informativo

AERONÁUTICA CIVIL
UNIDAD ADMINISTRATIVA ESPECIAL

VUELO AC2C3C
SEGUIMOS TRANSFORMANDO VIDAS Y SUEÑOS

Sistema de Vigilancia y Control Ambiental

Applus+ K2