BOLETÍN INFORMATIVO AMBIENTAL AEROPUERTO INTERNACIONAL EL DORADO

Centro de Monitoreo Aéreo Ambiental
II - 2023

Unidad Administrativa Especial de Aeronáutica Civil

Volumen 5

AERONÁUTICA CIVIL
Unidad Administrativa Especial

COLOMBIA POTENCIA DE LA VIDA

VUELO AC2C3C
SEGUIMOS TRANSFORMANDO VIDAS Y SUEÑOS

Applus+ K2

Centro de Monitoreo Aéreo Ambiental CMAA

AERONÁUTICA CIVIL
UNIDAD ADMINISTRATIVA ESPECIAL

Contenido

1 PROGRAMA DE MEJORAMIENTO PARA LA PREVENCIÓN DEL PELIGRO AVIARIO

2 SOCIALIZACIÓN CENTRO DE MONITOREO AEREO AMBIENTAL

3 TALLERES AMBIENTALES

4 ARTICULACIONES INTERINSTITUCIONALES

5 INSTALACIÓN DEL VIGÍA AMBIENTAL MUNICIPIO DE FUNZA

6 MECANISMOS DE PARTICIPACIÓN PQRS II-2023

7 ABC PLATAFORMA AEROVISION

AERONÁUTICA CIVIL
Unidad Administrativa Especial

COLOMBIA POTENCIA DE LA VIDA

VUELO AC2C3C
SEGUIMOS TRANSFORMANDO VIDAS Y SUEÑOS

Applus+ K2

Centro de Monitoreo Aéreo Ambiental CMAA

PROGRAMA DE PREVENCIÓN PELIGRO AVIARIO Y FAUNA EN ÁREAS EXTERNAS AL AEROPUERTO INTERNACIONAL EL DORADO

De acuerdo con la problemática que se identificó anteriormente, actualmente se desarrolla el programa de mejoramiento para la prevención de peligro aviario en las áreas externas del Aeropuerto Internacional El Dorado de Bogotá. De esta forma, el programa busca el control y/o mitigación de las áreas atractivas de fauna por medio las gestiones pertinentes, fundada en la información suministradas por las inspecciones y monitoreo permanentes del área de control del aeropuerto Internacional El Dorado, comprendido en un polígono de 13 km a partir de las cabeceras de las pistas y las superficies de aproximación.

Áreas de control de Peligro Aviario – Aeropuerto Internacional Eldorado

ESPECIE DE ALTO RIESGO

Gracias al programa de prevención de peligro aviario y fauna, actualmente se sabe que en el país hay al menos 127 especies de aves, incluyendo residentes y migratorias, que han tenido impactos con aeronaves. La mayoría de estas especies son pequeñas como atrapamoscas, golondrinas, semilleros y palomitas, que en términos generales no revisten peligro para la aviación con excepción de aquellas que forman bandadas grandes. Sin embargo, dentro de este grupo también hay aves grandes y medianas como chulos, gualas, águilas, alcaravanes y garzas, que tienen mayor probabilidad de causar daños estructurales a aviones, helicópteros y otras aeronaves.



Coragys atratus (chulos)
Fuente: Aerocivil
2024

Teniendo en cuenta que estos datos provienen de unos pocos aeropuertos de la extensa red de aeropuertos del país, y que se estima que estos corresponden a entre el 5% y el 10% de los impactos que ocurren en realidad, es posible hacerse una idea de la verdadera magnitud del peligro aviario en Colombia.

RIESGO PARA LA AERONAVEGACIÓN

Una de las especies de aves identificadas como especie de alto riesgo para la aeronavegación que representa peligro son los chulos (*Coragys atratus*), estas aves han sido registrados a una altura máxima reportada por los pilotos del aeropuerto internacional Augusto C. Sandino en Managua Nicaragua hasta los 1828.26 metros (6000 ft AGL), esto quiere decir que esta especie tiene un vuelo muy alto y puede poner en riesgo la operación aérea.

Sin embargo, algunas otras especies de aves generalmente vuelan muy bajo, en una franja que con frecuencia no supera los 30 metros AGL, por eso su abundancia es inversamente proporcional a la altitud.

Es decir, que las aves son más abundantes cerca del suelo, tal como lo ilustra la siguiente grafica.

Por esta razón la mayoría de los impactos entre aves y aeronaves ocurren dentro del aeropuerto, debido a que allí coinciden las bajas alturas de vuelo de ambos actores: aves y aeronaves; llegando hasta el 70% de los impactos, y el restante 30% ocurre fuera del aeropuerto. Técnicamente esto es definido por la altitud del impacto, de manera que si ocurre a altitudes inferiores a 500 ft AGL (pies sobre el nivel del suelo) se considera dentro del aeropuerto, y si ocurre a altitudes superiores entonces se considera que ocurrió por fuera.

Entonces, si bien la mayoría de los impactos ocurren al interior del aeropuerto (por tanto, es allí donde se toman las principales medidas) es un hecho preocupante que casi la mitad (45%) de los impactos con daños graves ocurren por fuera del aeropuerto debido a la energía cinética acumulada por la velocidad de las aeronaves. Por lo tanto, una gestión completa del riesgo debe contemplar no solo el interior aeroportuario, sino también el contexto externo de forma rigurosa y permanente

LA GESTIÓN SOCIAL Y PELIGRO AVIARIO

El programa de mejoramiento para la prevención del peligro aviario y fauna en áreas externas al aeropuerto Internacional el Dorado, cuenta con acción social para la contribución de la mitigación en áreas atractivas.

Se realiza el reconocimiento de las partes de interés y poder o actores claves del área de influencia del aeropuerto, y la identificación de condiciones socioeconómicas, culturales y políticas que subyacen en el territorio.

Se priorizaron, las localidades de Engativá, Fontibón y del Municipio de Funza, en las cuales se ha centrado principalmente las gestiones sociales, dado que, en estos territorios se ubican la mayor cantidad de sitios antrópicos atractivos para aves, identificados por el componente biótico.

ACCIONES INTERINSTITUCIONALES

A partir de la identificación de actores con interés, poder y corresponsabilidad en la prevención del riesgo por peligro aviario y, en consecuencia, con el nivel de riesgo de los sitios atrayentes de fauna determinados por el componente técnico, se concretan acciones interinstitucionales, especialmente en los sitios determinados como de alto y mediano riesgo; entre estas actividades se encuentran:

El reconocimiento en sitios de problemáticas en torno a la presencia de sitios atractivos para aves, operativos en lugares de acumulación de residuos, jornadas de sensibilización en sitios de manera articulada con entidades, comunidad, además del desarrollo de acciones de seguimiento, mesas de trabajo, y notificación a las entidades con competencia en acciones de control y gestión de sitios con acumulación de residuos.

Sabias Qué… Las actividades Interinstitucionales y el trabajo comunitario son un pilar fundamental para el desarrollo de las acciones que mitigan los riesgos e impactos.

AERONÁUTICA CIVIL
UNIDAD ADMINISTRATIVA ESPECIAL

PROGRAMAS COMUNITARIOS: "NIÑOS AVIARIOS" 2023

El programa de Niños Aviarios tiene como objetivo, generar espacios de conocimiento teórico prácticos en 4 módulos a 10 niños mediante prácticas ambientales que generen el ejercicio de la prevención del riesgo por situaciones evidenciadas, permitiendo asumir un rol de liderazgo en identificación y gestión de riesgos por fauna.

Entrega de Herramientas

Métodos y herramientas para observación de aves

Entrega KITS

Introducción

Biología básica de las aves .

02

03

04

Avistamiento

Ejercicio práctico de avistamiento en los Humedales

Presentación

Tema: gestiones de riesgo por fauna.

01

AERONÁUTICA CIVIL
UNIDAD ADMINISTRATIVA ESPECIAL

VUELO AC2C3C
SEGUIMOS TRANSFORMANDO VIDAS Y SUEÑOS

Applus+ K2

Centro de Monitoreo Aero Ambiental - CMAA

AERONÁUTICA CIVIL
UNIDAD ADMINISTRATIVA ESPECIAL

SOCIALIZACIÓN CENTRO DE MONITOREO AEREO AMBIENTAL EN LAS LOCALIDADES DE ENGATIVÁ, FONTIBÓN Y MUNICIPIO DE FUNZA

A partir de los canales de comunicación establecido por la Aeronáutica Civil, se desarrolló una citación a las diferentes comunidades del Área de Influencia del Aeropuerto Internacional El Dorado, con el objetivo de establecer las socializaciones en relación con la transición del Sistema de Vigilancia y Control Ambiental -SVCA al Centro de Monitoreo Aero Ambiental - CMAA, el cual potencializó la vigilancia y monitoreo ambiental.

Estos espacios se desarrollaron en bloques de encuentro, priorizando las unidades territoriales del área de Influencia del aeropuerto Internacional el Dorado.

Adicionalmente, para garantizar la participación de las comunidades se dispuso un enlace web para aquellos líderes y autoridades que quieran participar desde la virtualidad garantizando espacios

SOCIALIZACIÓN CENTRO DE MONITOREO AEREO AMBIENTAL - CMAA

En estos espacios de socialización se contó con la asistencia de 160 lideres comunitarios, los cuales hacen parte del área de influencia del Aeropuerto Internacional El Dorado, generando trasferencias de información de la Entidad a las comunidades.

Territorio	# Reuniones	# Asistentes
FUNZA	3	30
ENGATIVÁ	6	66
FONTIBÓN	6	58

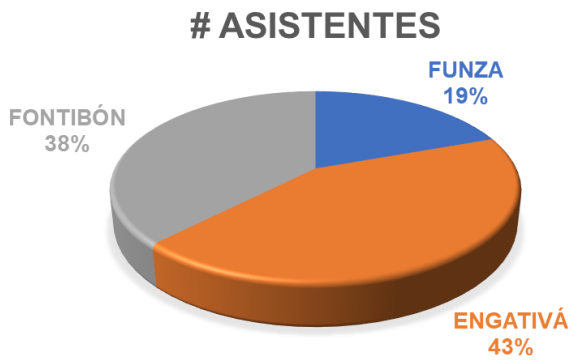

Forma de participación de las comunidades

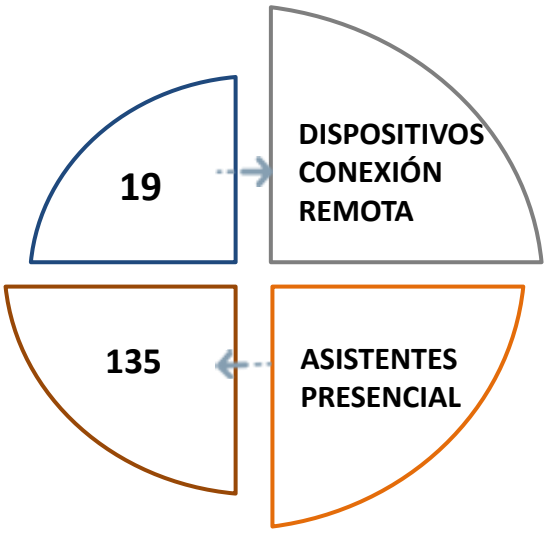

Las socializaciones se llevaron a cabo, de manera **virtual y presencial**, favoreciendo la participación e información de los lideres comunitarios de todas las unidades territoriales.

AERONÁUTICA CIVIL
UNIDAD ADMINISTRATIVA ESPECIAL

COMITÉ COMUNITARIO AEROPORTUARIO AEROPUERTO INTERNACIONAL EL DORADO

Este comité tiene como finalidad ejercer la veeduría a las actividades técnicas y sociales de la licencia Ambiental para el Aeropuerto Internacional El Dorado, establecido en la Resolución 1728 del año 2021. Es así que este espacio, busca la máxima representatividad democrática de las comunidades de las comunidades aledañas a la terminal Aérea.

Para el segundo perdido del 2023 se llevó el Comité Comunitario Aeroportuario, contando con la participación de 45 personas tanto presencial como virtual, de las Localidades de Fontibón, Engativá y el Municipio de Funza

Los temas tratados en este encuentro se establecieron según el interés de los participantes, los cuales se tornaron en la explicación del tena de Cuota de Ruido y Medidas de Mitigación del Ruido del Aeropuerto.

Cuota de Ruido

Medidas de Mitigación del Ruido

Inscríbete

Tu participación en este comité es importante. Si te interesa o quieres tener mayor información escríbenos al WhatsApp 310 280 3999

AERONÁUTICA CIVIL
UNIDAD ADMINISTRATIVA ESPECIAL

VUELO AC2C3C
SEGUIMOS TRANSFORMANDO VIDAS Y SUEÑOS

Applus+ K2

Centro de Monitoreo Aero Ambiental - CMAA

ARTICULACIONES INTERINSTITUCIONALES

Desde el grupo de Gestión Ambiental y Control Fauna de la Entidad, se mantienen los acercamientos y convenios con diferentes instituciones públicas y privadas, con el objetivo de promover acciones coordinadas interinstitucionalmente en beneficio y atención a las comunidades del área de influencia, según las competencias y objetivos misionales de cada entidad.

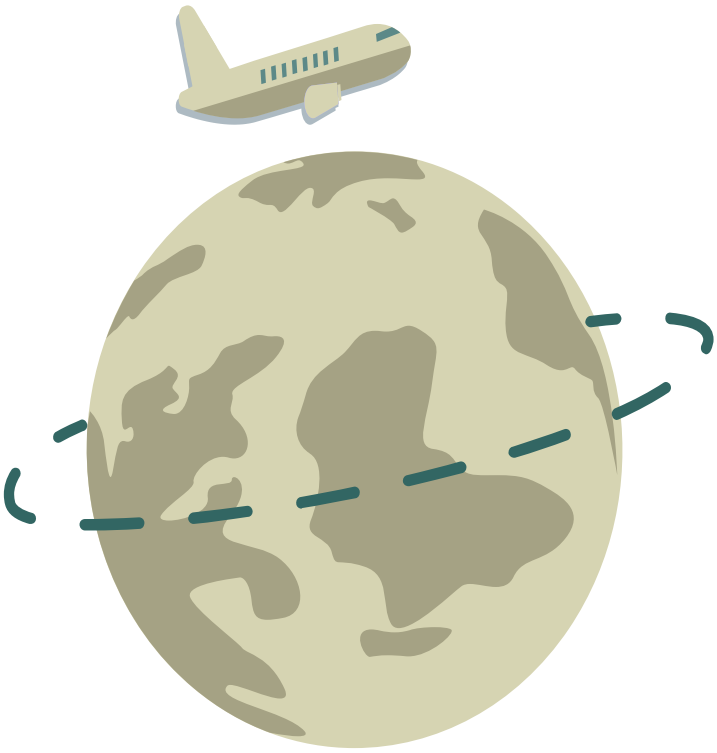

- OPAIN
- CRUZ ROJA
- FAC
- IDRD
- HELISTAR

Estos convenios conllevan al reconocimiento del entorno y apropiación del territorio para las comunidades vecinas de la terminal aérea, desde los talleres de agricultura, ferias de emprendimientos locales, visitas al museo aeroespacial, talleres saludables y capacitaciones en primeros auxilios.

ARTICULACIONES INTERINSTITUCIONALES

Fortalecimiento a Huertas Comunitarias

En el barrio La Zelfita Fontibón. La articulación con la Aerolínea Helistar, se realizo el **Encerramiento del segundo tramo Huerta Zelta Chie-,** que se adelanto con la Aeronáutica Civil.

Deporte con el adulto mayor. Esta articulación se realiza con el Instituto Distrital de Recreación y Deporte. Estas actividades se llevaron a cabo, en el barrio San Joaquín Norte, Engativá, con una asistencia cerca de **50 personas**

ARTICULACIONES INTERINSTITUCIONALES

Visita Museo Aeroespacial, Localidades de Engativá y Fontibón- Convenio Fuerzas Aéreas Colombianas. Las visitas se realizaron en los meses de Agosto y Noviembre con las comunidades de Engativá y Fontibón. Para un total de **65 asistentes**

Feria de Emprendimiento en el Aeropuerto Internacional El Dorado, **convenio OPAIN**. Participaron **25 emprendimientos** de las Localidades de Fontibón y Engativá. Este ejercicio se realiza con el apoyo de las **Autoridades Locales**

CAPACITACIÓN BRIGADA DE EMERGENCIA

Se realiza la gestión para la capacitación de 40 personas del AI de las Localidades de Engativá y Fontibón, con una formación en Brigadistas de Emergencia en la Cruz Roja. Este encuentro se llevó a cabo en el mes de Noviembre del año 2023.

Este evento se realizó en las instalaciones del Centro de Innovación y Entrenamiento en Gestión del Riesgo de Desastres –CIGER- de la Cruz Roja, en el municipio de Tabio Cundinamarca.

Como parte del contenido del curso, los asistentes recibieron capacitación en:

- Protocolo básico de atención inicial.
- Lesiones en tejidos blando y óseo.
- Conformación de brigadas de emergencia.
- Fases de evacuación.
- Prevención de fuego.
- Clases de fuego.
- Tipos de extintores.

AERONÁUTICA CIVIL
UNIDAD ADMINISTRATIVA ESPECIAL

CICLO AMBIENTAL
RECUPERACIÓN DEL VIDRIO

A comienzos del 2023, se inaugura el Ciclo Ambiental el cual tiene como objetivo favorecer al medio ambiente y las comunidades, fomentando la economía circular y sostenible de los grupos participantes. Este esta enfocado a la recuperación del vidrio y consta de tres procesos:

1. Reutilización "Taller de Terrarios"
2. Reciclar "Taller de Creación de velas"
3. Recuperación "Taller de corte de Botellas"

ASÍ LO HACEMOS

MARCACIÓN

Se marca la botella de vidrio con un corta vidrios

CORTADO

Seguido, se realiza la exposición al calor y el frio para provocar el corte.

Corte de Botellas

LIJADO

Para evitar grietas se pule con lijas entre 100, 200 y 400

DECORACIÓN

Finalmente, se decora al gusto

Con esta propuesta se pretende, iniciar procesos sociales que se mantengan en el tiempo, realizando un debido acompañamiento a las poblaciones y a su vez, poder establecer lazos de confianza entre la Aeronáutica Civil y las comunidades.

AERONÁUTICA CIVIL
UNIDAD ADMINISTRATIVA ESPECIAL

VUELO AC23
SEGUIMOS TRANSFORMANDO VIDAS Y SUEÑOS

Applus+ K2

Centro de Monitoreo Aero Ambiental - CMAA

TALLERES AMBIENTALES

Los talleres ambientales permitieron a los participantes durante este periodo, reconocer aspectos como la creatividad y trabajo en grupo, arrojando como resultado acercamiento a La Entidad y expectativas frente a los demás temas que hacen parte del proceso de recuperación de vidrio

La finalidad de estos espacios es generar herramientas para la creación de ideas de reutilización del vidrio, ampliando el conocimiento y conciencia ambiental; ya que, al reciclar, reducir y reutilizar, se generan grandes beneficios para el medio ambiente, como la disminución de residuos sólidos, hasta un beneficio económico, creando emprendimientos relacionados con estas actividades.

En cuanto a la recepción por parte de los asistentes, mencionan que estos espacios contribuyen no solo al esparcimiento y socialización con los vecinos, sino también a potenciar sus capacidades y conocimientos, así mismo, a generado puntos focales informativos directos con la Entidad y para discutir temas relacionados sobre la operación del Aeropuerto Internacional El Dorado y el funcionamiento del CMAA.

VIGÍA AMBIENTAL EN EL MUNICIPÍO DE FUNZA

Durante el segundo semestre de 2023 se tramitaron permisos de uso del suelo e instalación del vigía ambiental en el municipio de Funza, con el objetivo de instalar en las comunidades un instrumento de visualización de datos de ruido y contaminación atmosférica en tiempo real.

En el mes de diciembre de 2023 con los permisos concedidos por las entidades competentes, se realizó instalación. Finalmente se inauguró la obra y activó el vigía Ambiental el día 22 de diciembre de 2023.

MECANISMOS DE PARTICIPACIÓN CIUDADANA

No sabes donde, ni como interponer una Petición, Queja, Reclamación o Denuncia?

La Aeronáutica Civil te cuenta cuales son siguientes Mecanismos de Participación Ciudadana Para Interponer una PQRS.

Oficina de Atención al Ciudadano	• Av. Eldorado 103-15 • 1er Piso
Línea Telefónica	• PBX: (571)4251000 • Línea Gratuita: 018000112373
Profesionales de Campo	• Engativá 310 280 3999 • Fontibón 320 9163105 • Funza 3209163131
Buzones Veredales	Alcaldía de Funza, Sector San Isidro, Cancha de Tejo El Hato, Tienda Km 2 y Tienda Nueva
Sistemas Digitales	• **Pagina Web:** https://www.aerocivil.gov.co/atencion/atencionpqrd • **Correo Electrónico** atencionalciudadano@aerocivil.gov.co

PQRS
SEGUNDO SEMESTRE 2023

Durante el segundo semestre 2023 (junio a diciembre), se recibieron y tramitaron un total de 75 Solicitudes por parte de la comunidad. La mayoría de dichos requerimientos establecieron los siguientes temas: Ruido por sobrevuelos y operaciones aéreas, especialmente en las localidades: Suba y Fontibón.

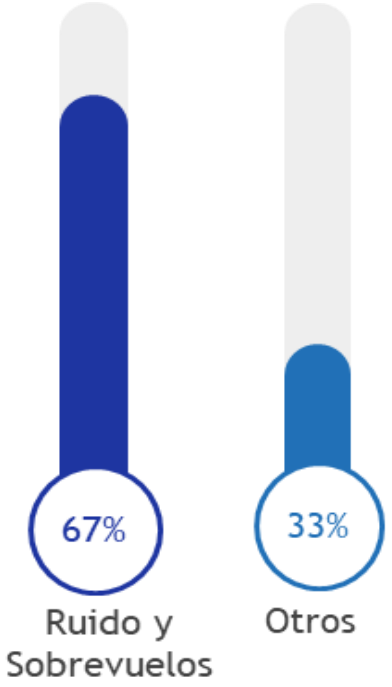

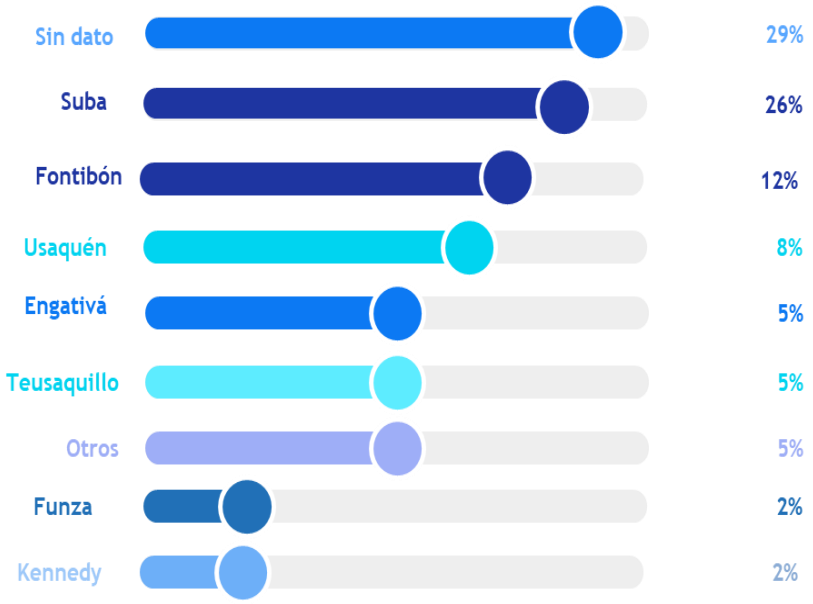

El trámite de PQRS requiere un trabajo permanente por parte del equipo de profesionales del CMAA, garantizando que las respuestas emitidas sean claras y satisfactorias para los peticionarios; por ello, se realizó atención personalizada mediante visita técnica a algunas solicitudes.

VISITA TÉCNICO-SOCIAL

En el marco de las visitas técnico-social para la atención de peticiones, quejas, reclamos y solicitudes funciona de la siguiente manera:

1. **La Entidad designa un(a) Gestor(a) Social**, durante la ejecución del proyecto del CMAA, quien establece y legitima la relación directa y permanente con el peticionario.

2. El Gestor(a) Social realizará **concertación con el peticionario** para establecer lugar, días y horas de atención.

3. **Las PQRS deberán cumplir con los siguientes pasos:**
   - Datos del solicitante (nombre, correo electrónico y/o Teléfono)
   - Incluir información como fecha y hora del evento

4. **Atención a la PQRS**
   - Apertura del trámite.
   - Valoración del evento
   - Acciones para atender la solicitud
   - Seguimiento a la respuesta.
   - Verificación de la entrega a la respuesta del peticionario.
   - Cierre del proceso.

Dependiendo del tipo de solicitud se establecerá un plazo en el marco de la Ley Colombiana, que puede ir de 15 a 30 días hábiles para dar respuesta oficial de la PQRS al peticionario.

EL ABC PLATAFORMA AEROVISION

Aerovision es una plataforma web que permite visualizar la información de ruido aeronáutico del Aeropuerto Internacional el Dorado. Proporciona todas las herramientas necesarias para el seguimiento, el análisis y la comunicación sobre el impacto de ruido medioambiental. A continuación se presenta un paso a paso para el uso por parte de la comunidad:

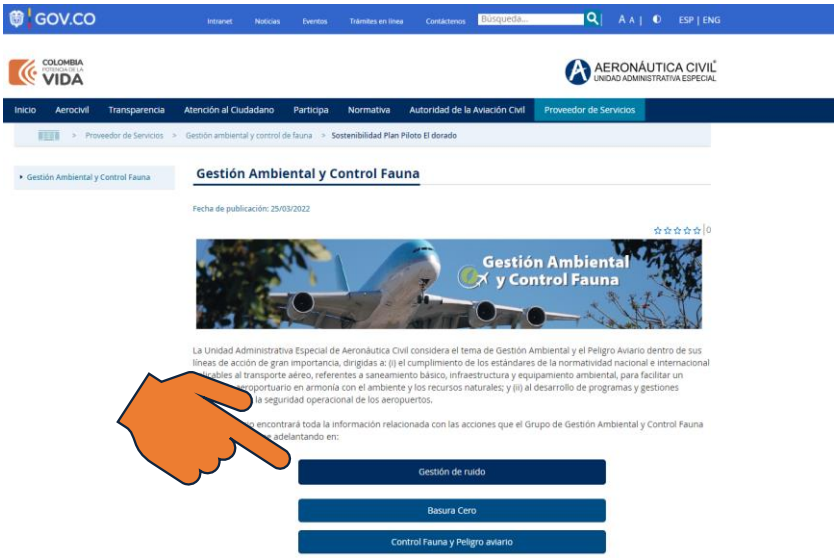

Enlace: https://www.aerocivil.gov.co/servicios-a-la-navegacion/gestion-ambiental-y-control-de-fauna/Plan-Piloto-ElDorado/resoluciones-anla-plan-piloto

Al dar clic en Gestión de ruido, se abrirá la página donde se explica las acciones y programas que se están ejecutando para la mitigación de ruido en los entornos aeroportuarios, implementando innovación y elementos de información tecnológica ambiental a nivel mundial, dado nuestro compromiso de una aviación ambientalmente sostenible.

Este enlace nos conduce a la plataforma web Aerovision donde encontramos un mensaje de bienvenida, que nos aclara que todos los datos que aparece en esta plataforma son informativos.

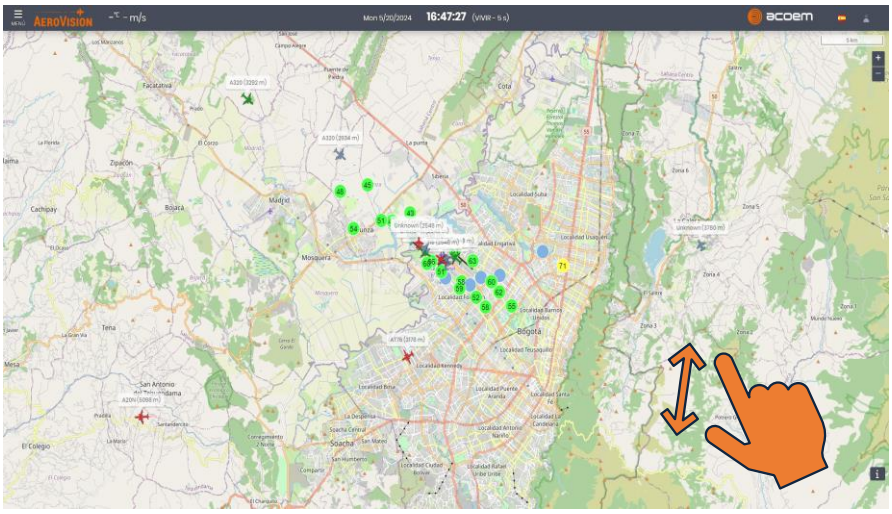

Al hacer esto podemos observar la en la pantalla las aeronaves que están realizando operaciones en tiempo real, con un retraso estimado de 5 segundos.

Aerovision permite conocer el nivel de ruido en tiempo real de las aeronaves que operan en el aeropuerto Internacional El Dorado.

Ruido
Nivel de Ruido de las Estaciones (dBA) EMRI

Altitud
Altitud de las Aeronaves

Modelo Aeronaves

Sitio Sobrevuelo
Ubicación de las Aeronaves

Identificación
Llegada Aeronaves: Verde
Salida Aeronaves: Rojo

NOTAS:

AERONÁUTICA CIVIL
UNIDAD ADMINISTRATIVA ESPECIAL

Boletín Informativo Ambiental

Unidad Administrativa Especial de Aeronáutica Civil

Volumen 5

AERONÁUTICA CIVIL
Unidad Administrativa Especial

VUELO AC2C3C
SEGUIMOS TRANSFORMANDO VIDAS Y SUEÑOS

COLOMBIA POTENCIA DE LA VIDA

Applus+ K2

Centro de Monitoreo Aéreo Ambiental CMAA